COMPENDIO DE GRÁFICAS 2D

Indicador | SFE−VTIN

Valor de la tierra | Zona de invernada

Fuente primaria

Revista Márgenes Agropecuarios

Unidad de medida

Dólares constantes de 1982 por ha de referencia

Último dato disponible

2026.M3

Fecha de actualización

04/03/2026

SFE−VTIN | SERIE ORIGINAL: DATOS BRUTOS TRANSFORMADOS

Fecha último dato [2026.M3]

Útimo dato: 3.612,94

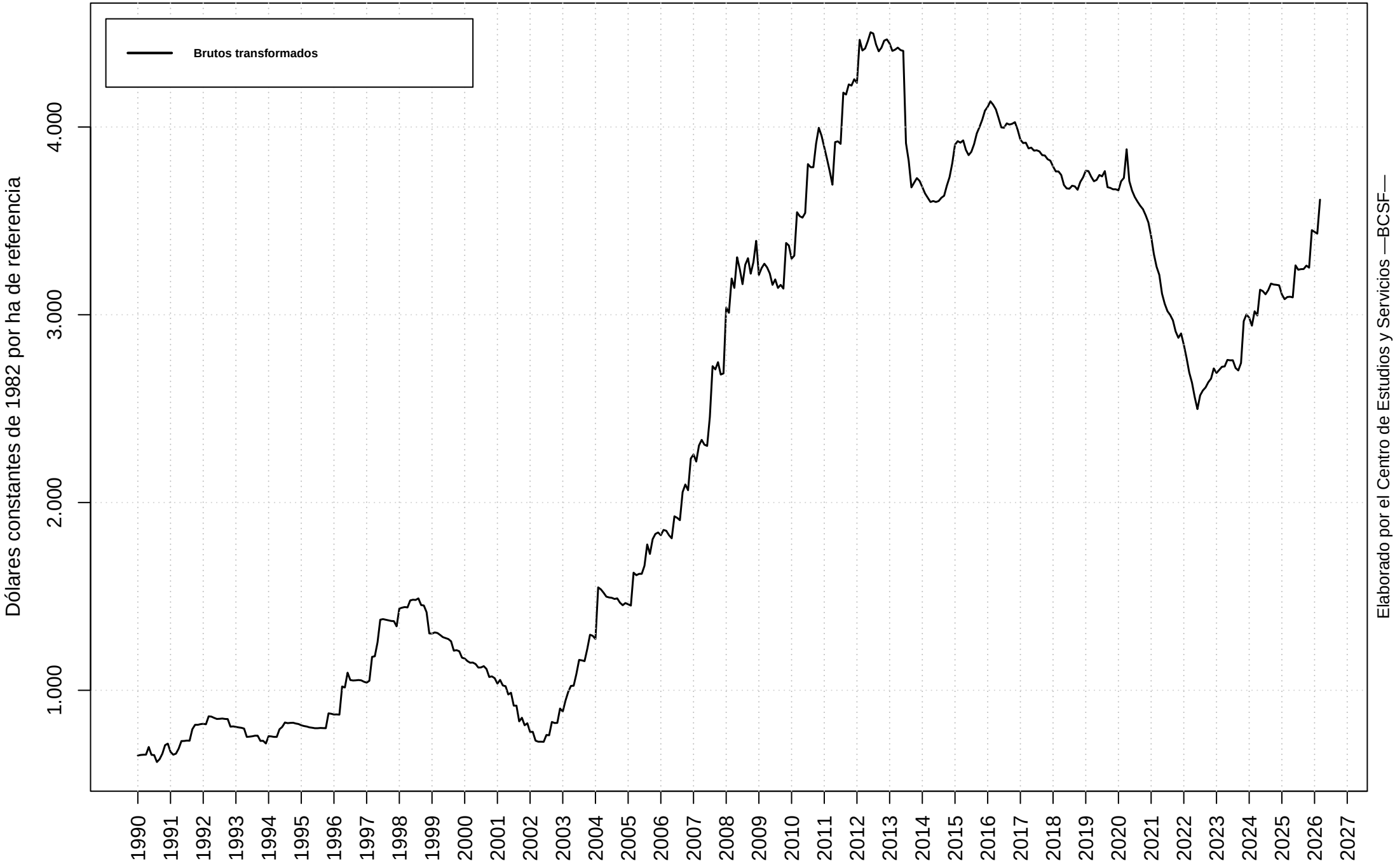

SFE−VTIN | MODELO DE AJUSTE: MEJOR LOGARITMO Y MEJOR NIVEL

Fecha último dato [2026.M3]

Modelo con menor volatilidad: log

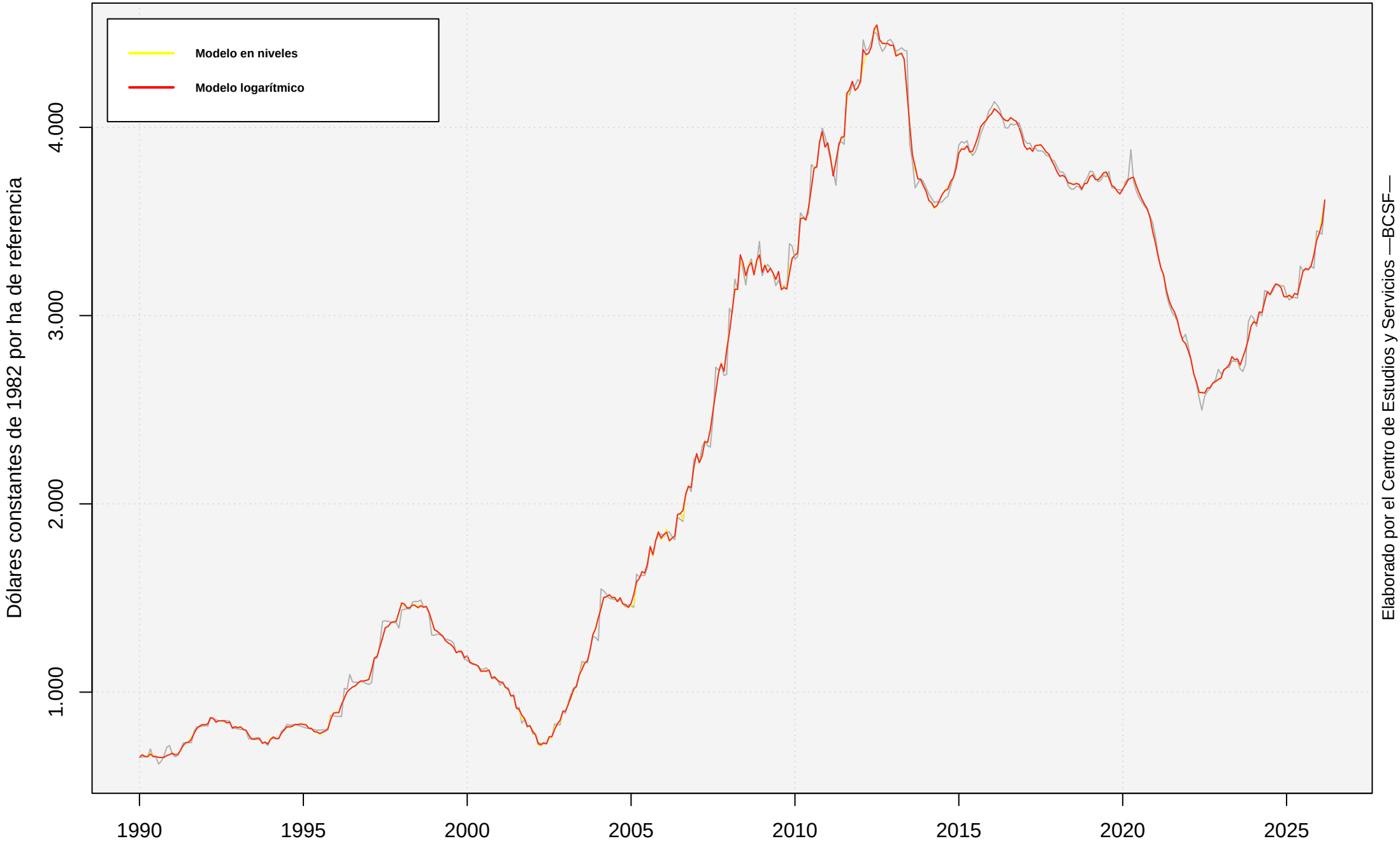

SFE−VTIN | SERIE ORIGINAL Y FILTROS

Fecha último dato [2026.M3]

Método: X11 | Transformación: log | Modelo: (1 1 1)

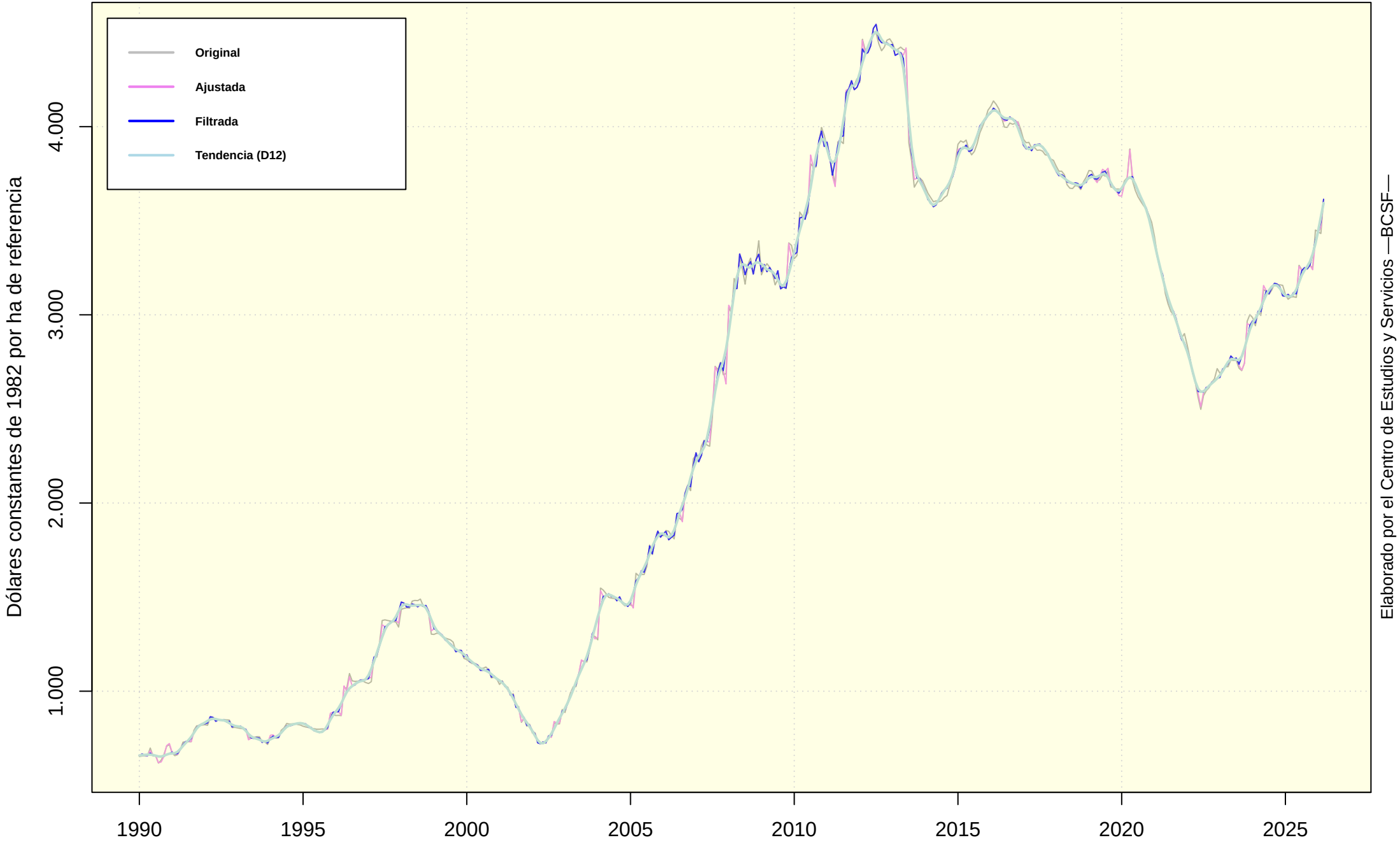

SFE−VTIN | VARIACIONES INTERANUALES

Fecha último dato [2026.M3]
Variación interanual último dato disponible: 15,1278 %

Media TCIA LP: 5,8742 %
Mediana TCIA LP: 5,0715 %

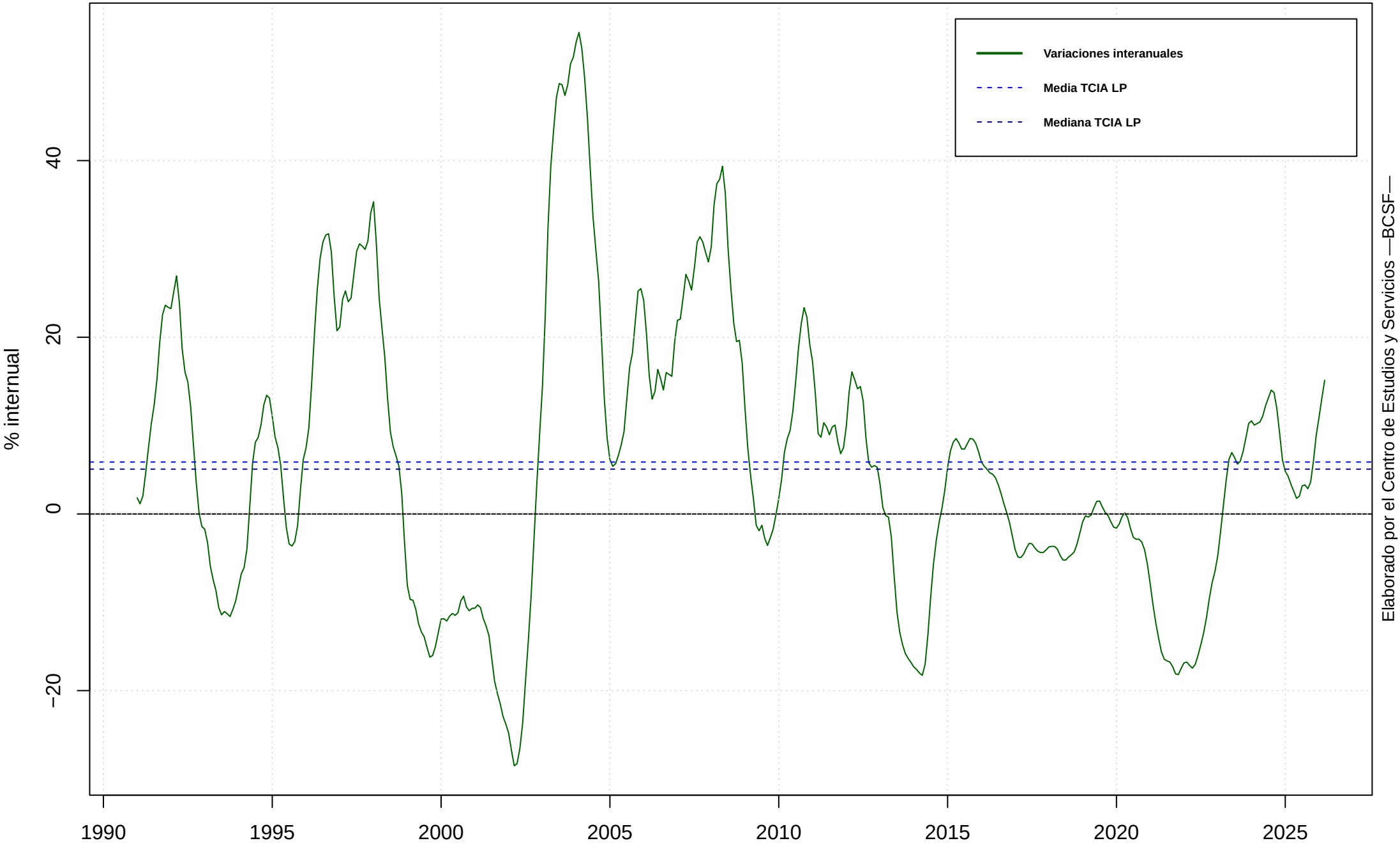
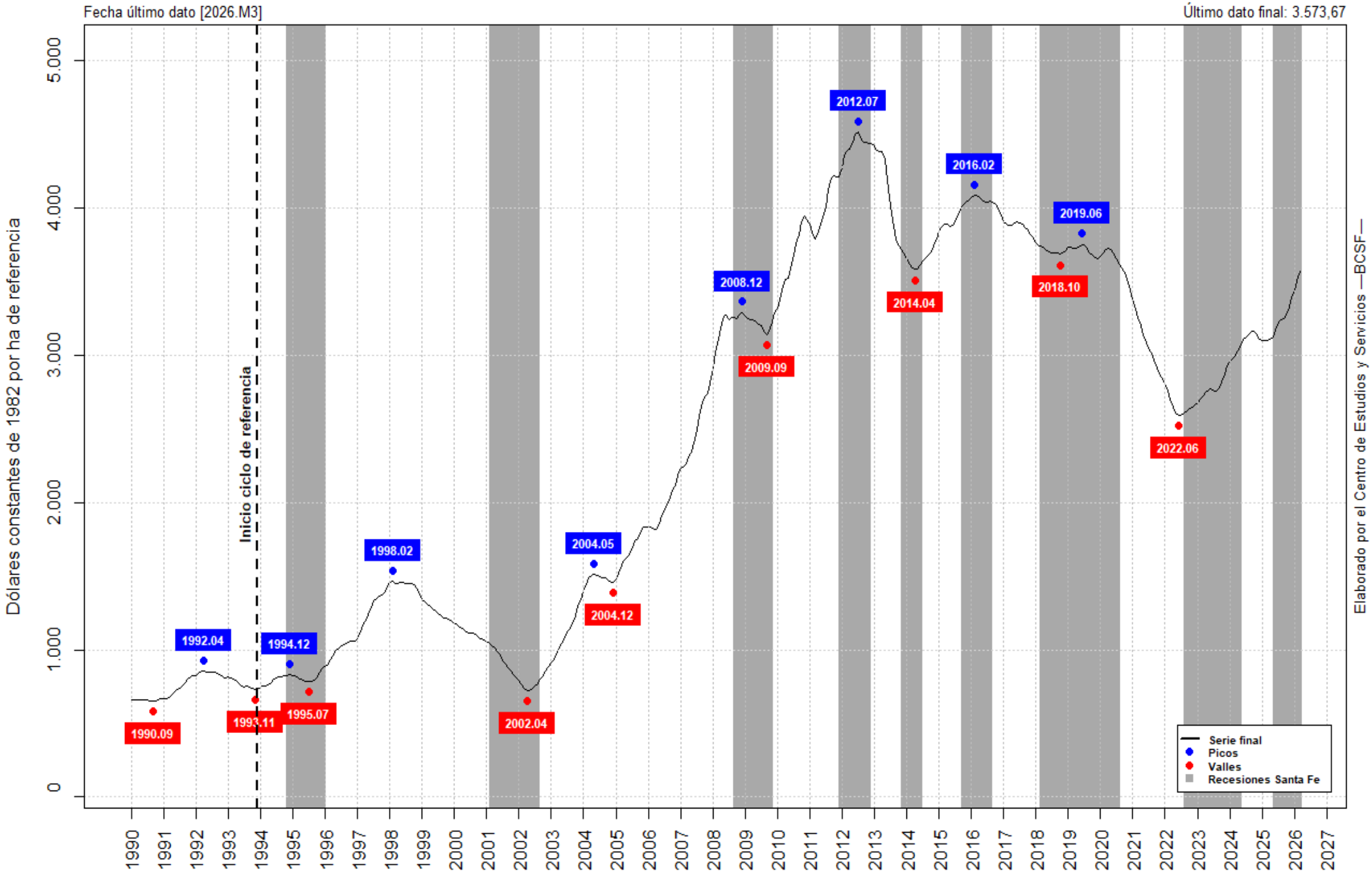
SFE-VTIN | SERIE FINAL Y GIROS