COMPENDIO DE GRÁFICAS 2D

Indicador | SFE−VTMA

Valor de la tierra | Zona maicera

Fuente primaria

Revista Márgenes Agropecuarios

Unidad de medida

Dólares constantes de 1982 por ha de referencia

Último dato disponible

2026.M3

Fecha de actualización

04/03/2026

SFE−VTMA | SERIE ORIGINAL: DATOS BRUTOS TRANSFORMADOS

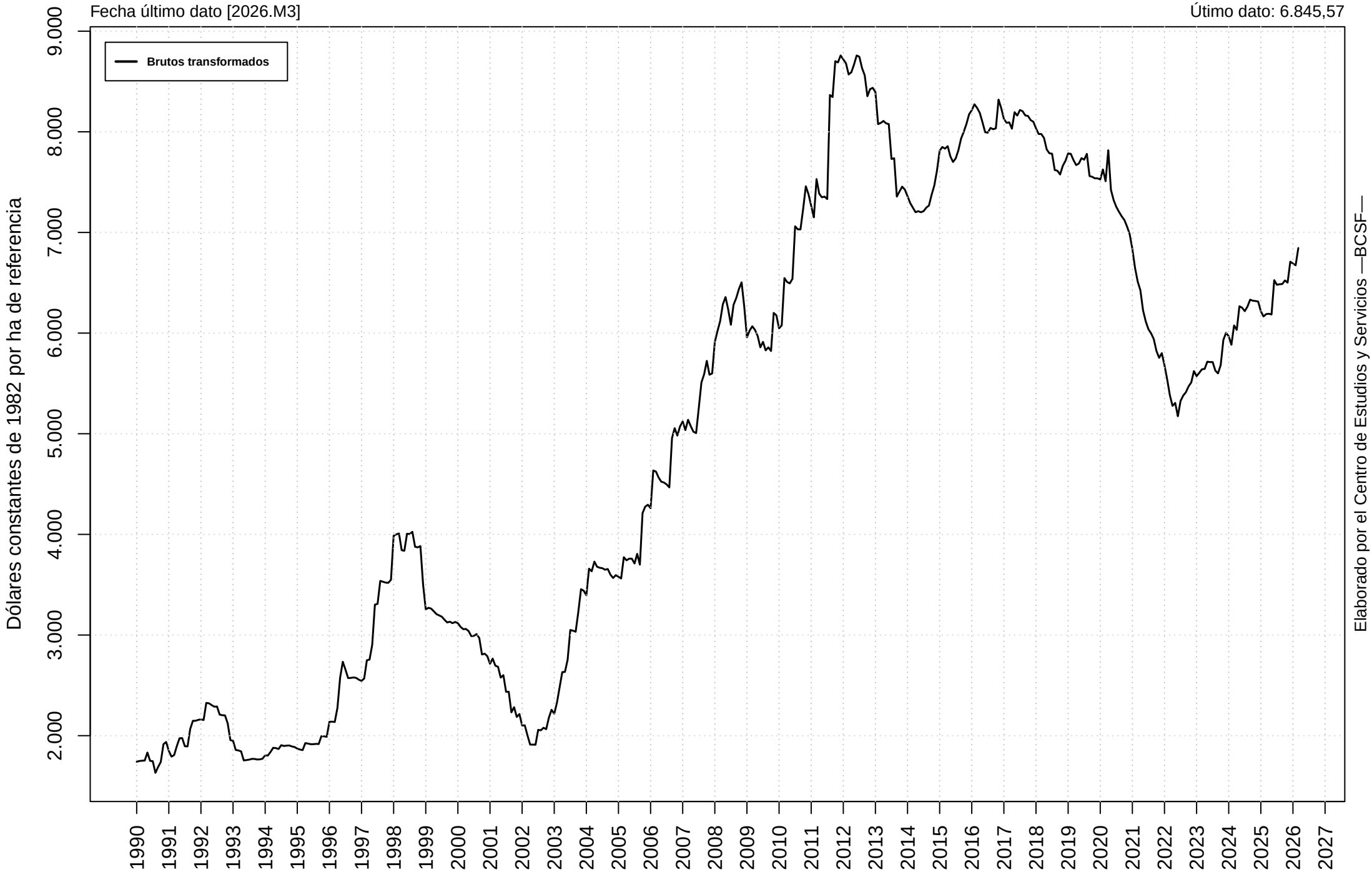

SFE−VTMA | MODELO DE AJUSTE: MEJOR LOGARITMO Y MEJOR NIVEL

Fecha último dato [2026.M3]

Modelo con menor volatilidad: log

SFE−VTMA | SERIE ORIGINAL Y FILTROS

Fecha último dato [2026.M3]

Método: X11 | Transformación: log | Modelo: (1 1 1)

SFE−VTMA | VARIACIONES INTERANUALES

Fecha último dato [2026.M3]
Variación interanual último dato disponible: 9,6874 %

Media TCIA LP: 4,9721 %
Mediana TCIA LP: 3,2667 %

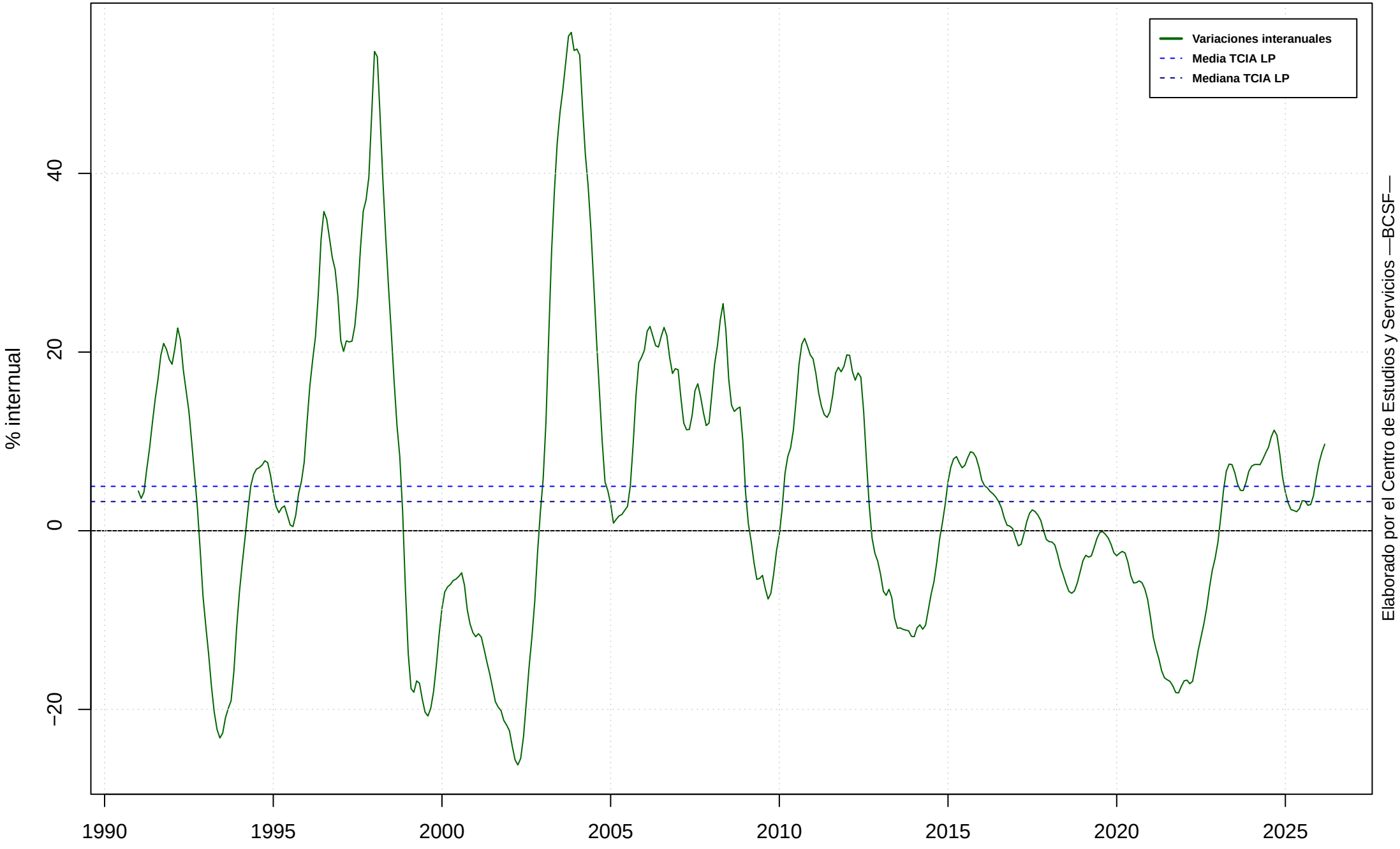
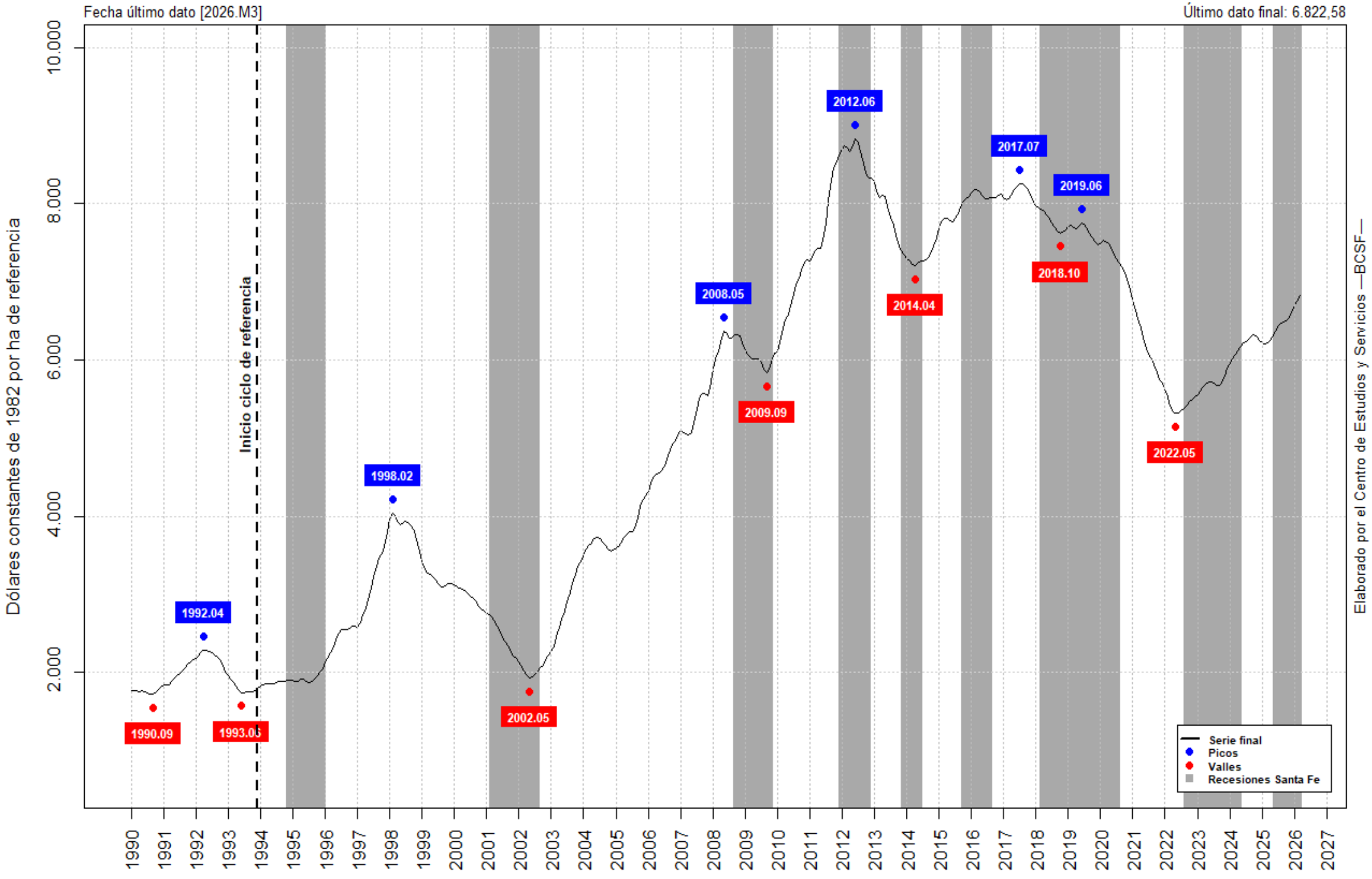
SFE-VTMA | SERIE FINAL Y GIROS